Cheikh BA • Anne BOUHALI • Adrien DORON • Claude GRASLAND • Aliou NDAO • Labaly TOURE

Combiner méthodes qualitatives et quantitatives pour l'analyse de cartes mentales : retour d'expérience du projet pédagogique franco-sénégalais Altermap

GÉOGRAPHIE, HISTOIRE, ÉCONOMIE ET SOCIÉTÉS
Sociétés et Humanités
Université Paris Cité

Plan

A. Les racines et objectifs du projet Altermap

B. Les axes d’expérimentation de la phase test

C. Les limites et les perspectives

A. Les racines et les objectifs du projet Altermap

Altermap En bref Equipe Groupes de travail Blog

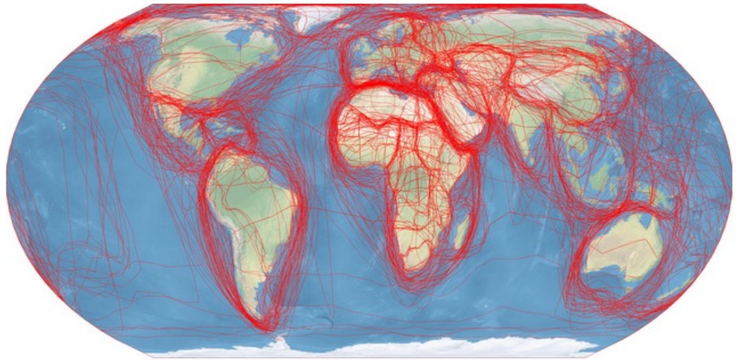

ALTERMAP

Méthodes qualitatives et quantitatives pour l'étude des cartes mentales et des représentations de l'altérité en Europe et en Afrique.

A. Les racines et les objectifs du projet Altermap

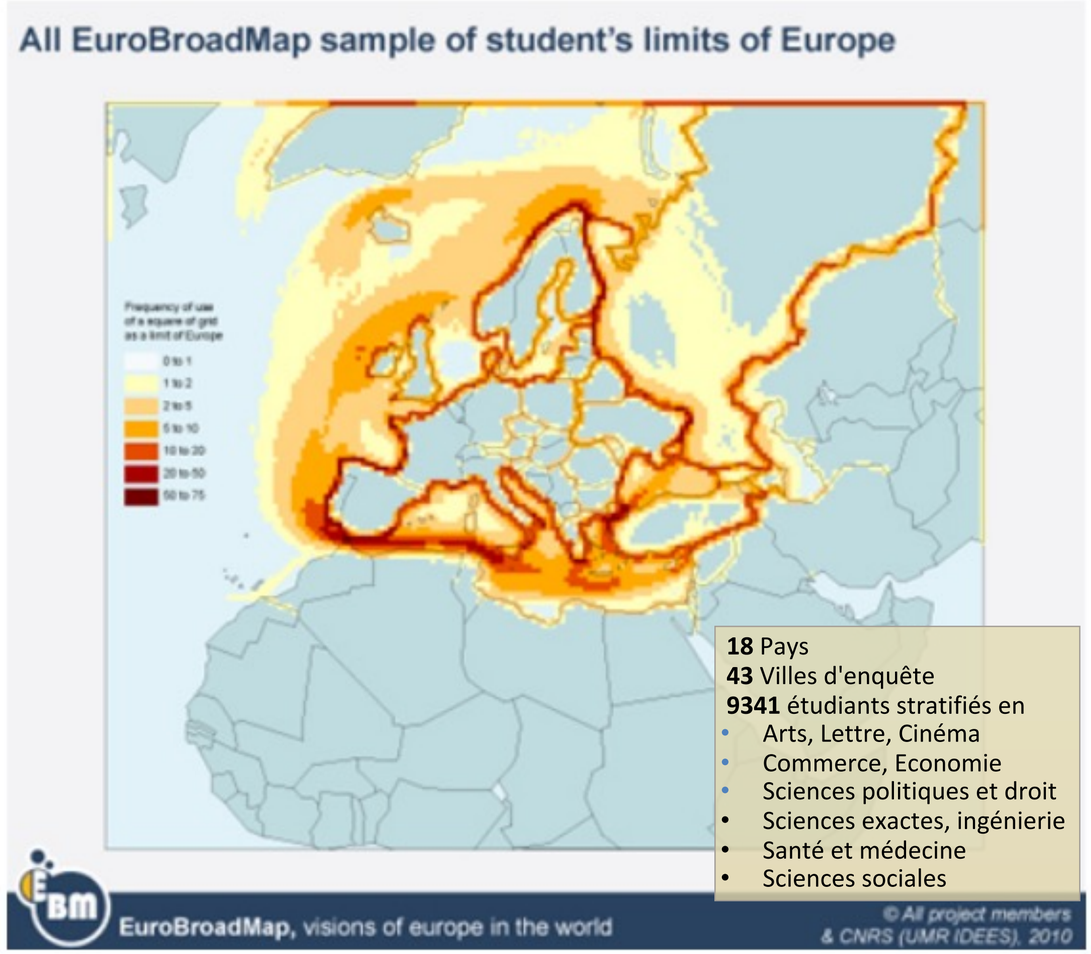

18 Pays
43 Villes d'enquête
9341 étudiants stratifiés en
- Arts, Lettre, Cinéma
- Commerce, Economie
- Sciences politiques et droit
- Sciences exactes, ingénierie
- Santé et médecine
- Sciences sociales

Clarisse Didelon, Sophie de Ruffray, Claude Grasland. Mental maps of students - Volume 1. 2011. ⟨halshs-00654521⟩

Carte sensible réalisée en collaboration avec **3** militant·e·s habitant·e·s de Marseille
Olmedo, É. (2019). Cartographie sensible des luttes. Vacarme, 89(4), I-II. https://doi.org/10.3917/vaca.089.0000
e

A. Les racines et les objectifs du projet Altermap

Objectifs pédagogiques opérationnels du projet :

(1) instaurer un dialogue parmi les formateurs entre des méthodologies qualitatives et quantitatives

(2) partager les résultats de ce dialogue entre chercheurs et enseignants-chercheurs d'un pays européen et d'un pays africain dans l'idée de renforcer nos partenariats franco-sénégalais

Un premier retour critique sur une expérience préliminaire de cinq mois (février-juin 2026), à la fois méthodologique et pédagogique : questionnements, construction collaborative, tâtonnements, limites.

B. Les axes d'expérimentation de la phase test

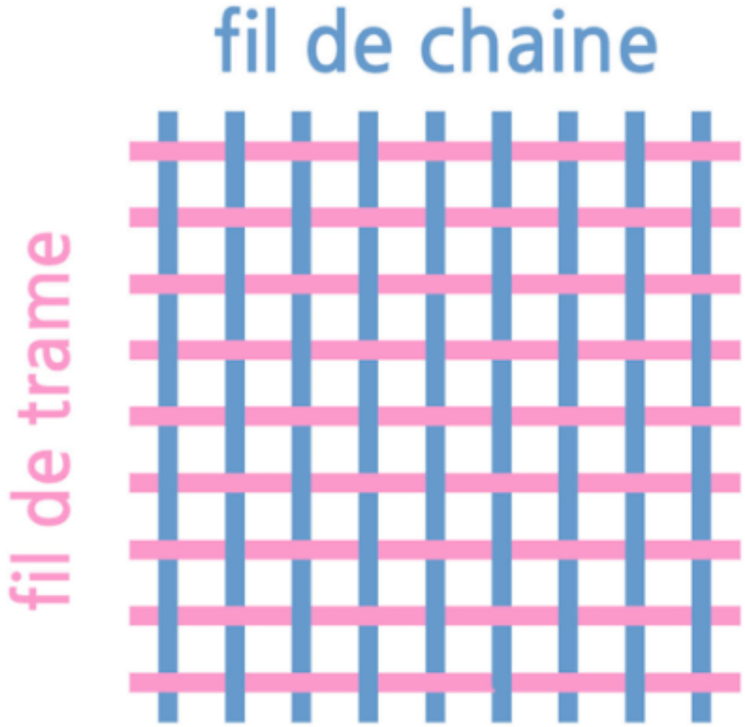

Axe1 : Représentations et découpages du Monde	Axe 2 : Représentation des limites de l'urbain et du rual	Axe 3 : Changement climatique et des vulnérabilités	Axe 4 : Régions, maillages et gouverance

Approches quantitatives – questionnaires – analyse textuelle – découpages sur support cartographique (sketch maps) - Localisations subjective et mesures objectives ...

Axe 5 : Trajectoires de vie et mobilité des étudiants	Axe 6 : Habiter la ville : pratiques urbaines, inégalités

Approches qualitatives – entretiens –
- cartes sensibles - émotions –
- trajectoires sur papier blanc -
approches non directives – focus group ...

B. Les axes d'expérimentation de la phase test

Axe 1: Découpages du Monde

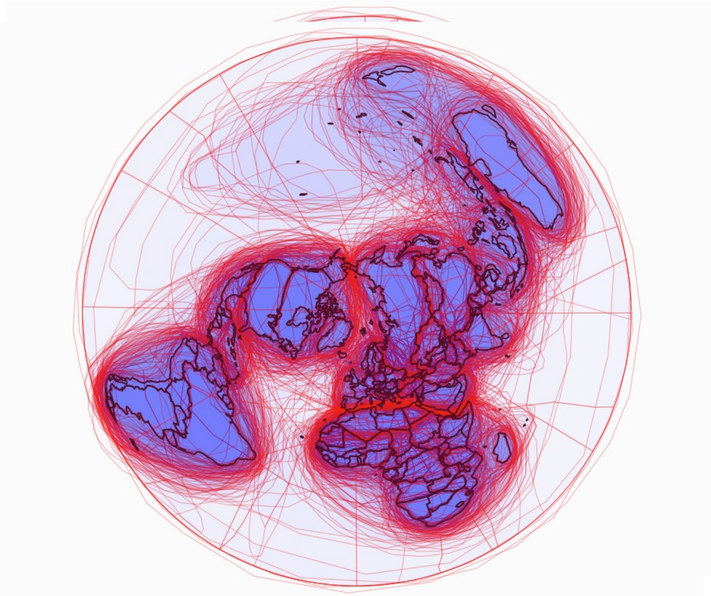

USSEIN – Kaolack
L3 Géomatique
87 étudiants

Université Paris Cité
L3 Géographie
61 étudiants

Axe 4: Découpages du Sénégal

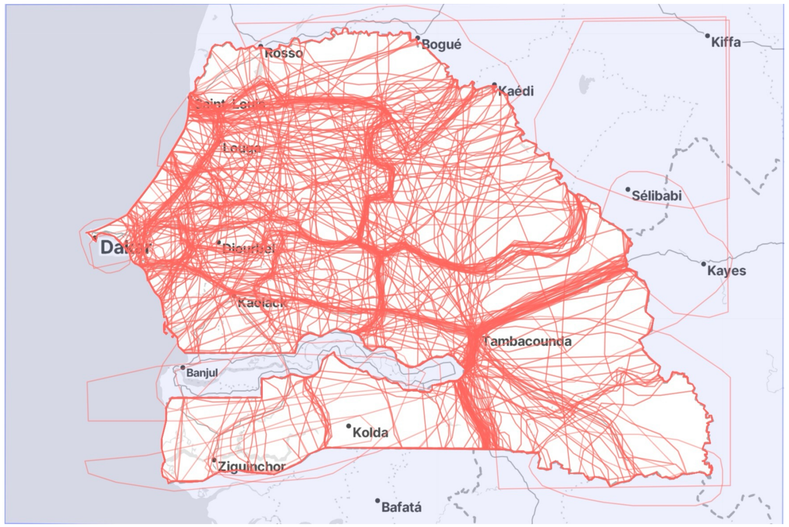

UCAD-Dakar
L1- Géographie
40 étudiants

IGTDL-Dakar
L2 - Gouvernance
25 étudiants

UGB – Saint-Louis
L3- Géographie
27 étudiants

B. Les axes d'expérimentation de la phase test

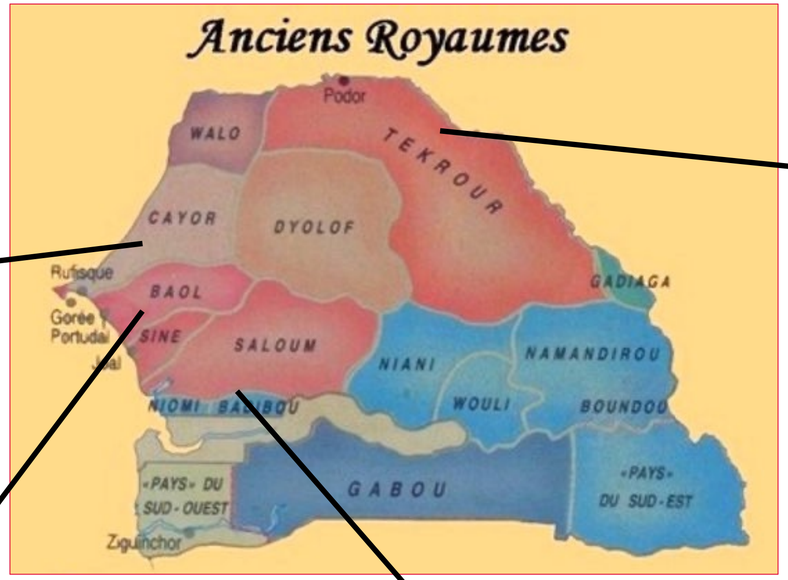

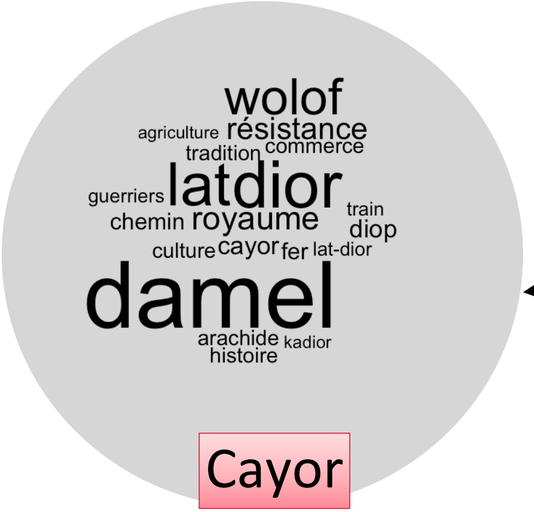



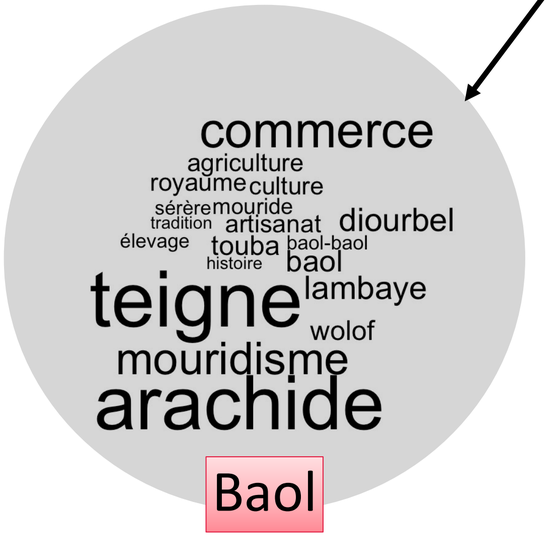

B. Les axes d'expérimentation de la phase test

LES MOTS DE L'EUROPE

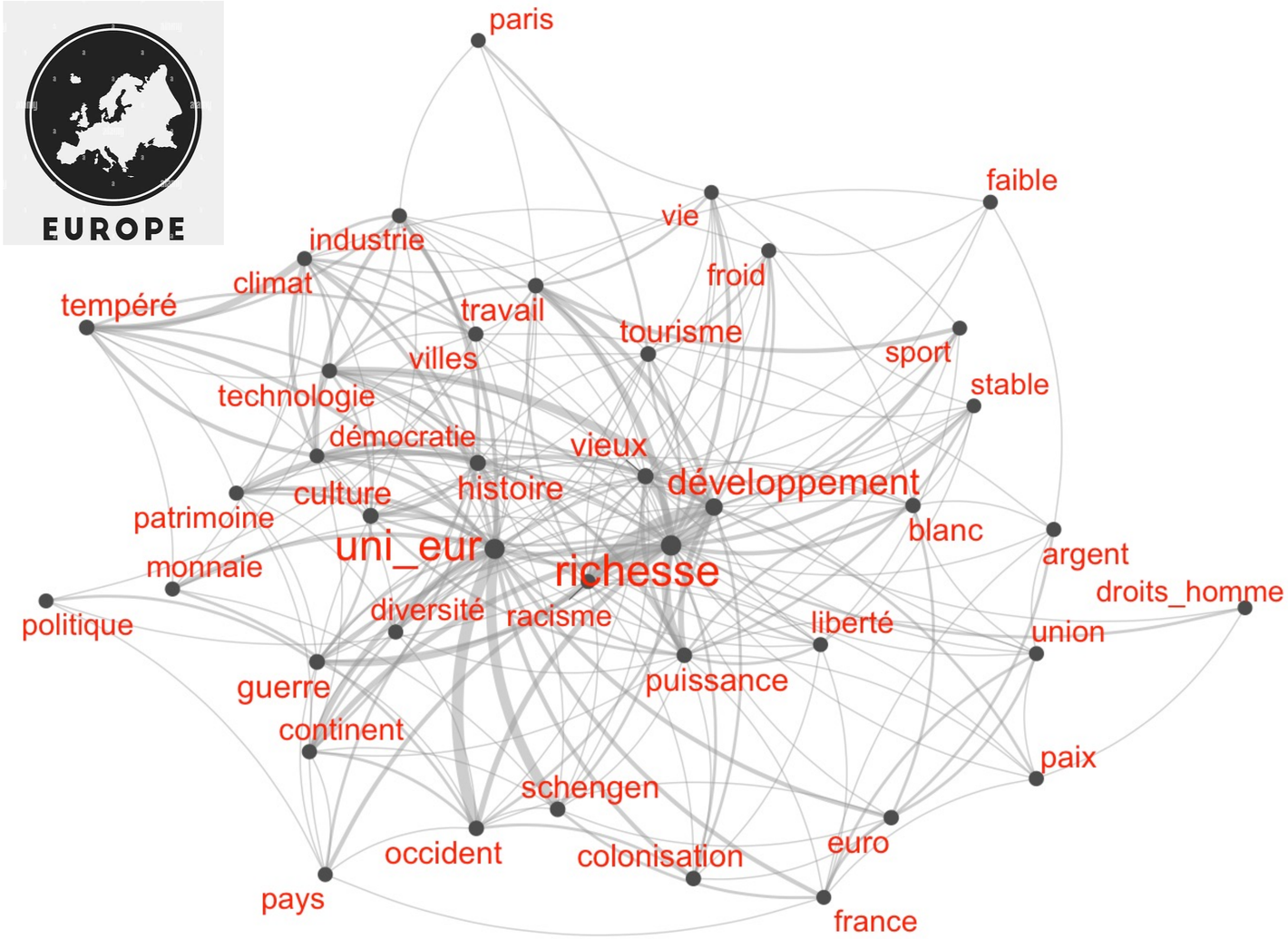

Paris ou Kaolack ?

PARIS

KAOLACK

B. Les axes d'expérimentation de la phase test

LES MOTS DE L'AFRIQUE

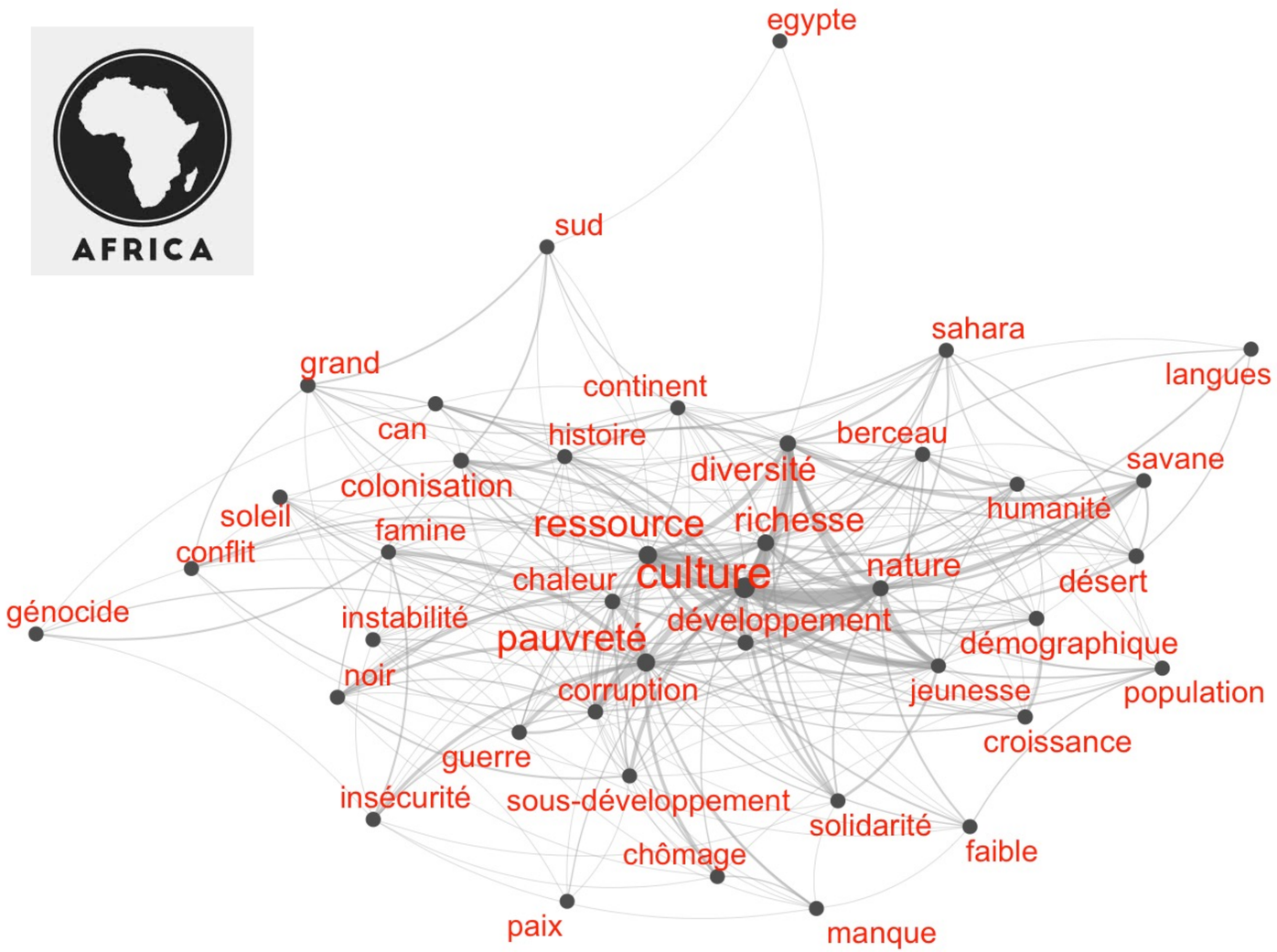

Paris ou Kaolack ?

KAOLACK

PARIS

B. Les axes d'expérimentation de la phase test

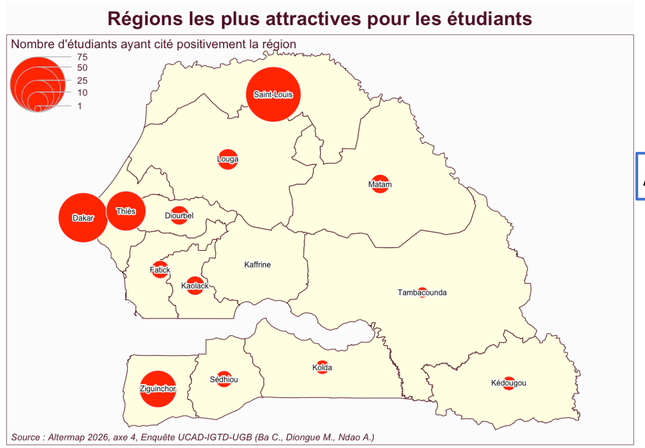

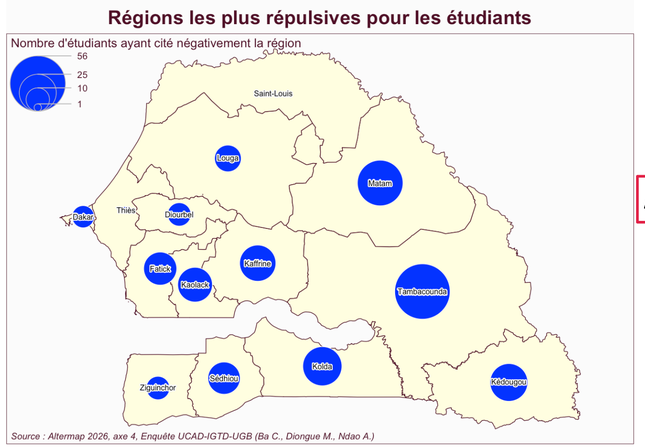

Avis positifs

Avis partagés

Avis négatifs

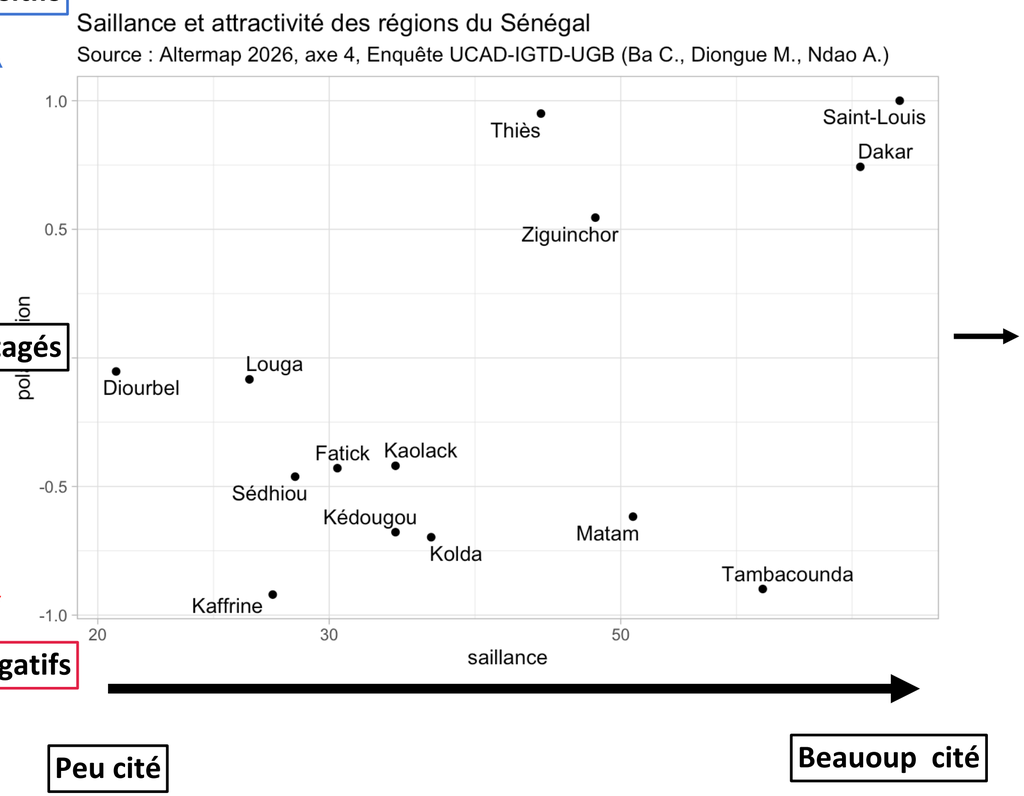

Peu cité

Beauoup cité

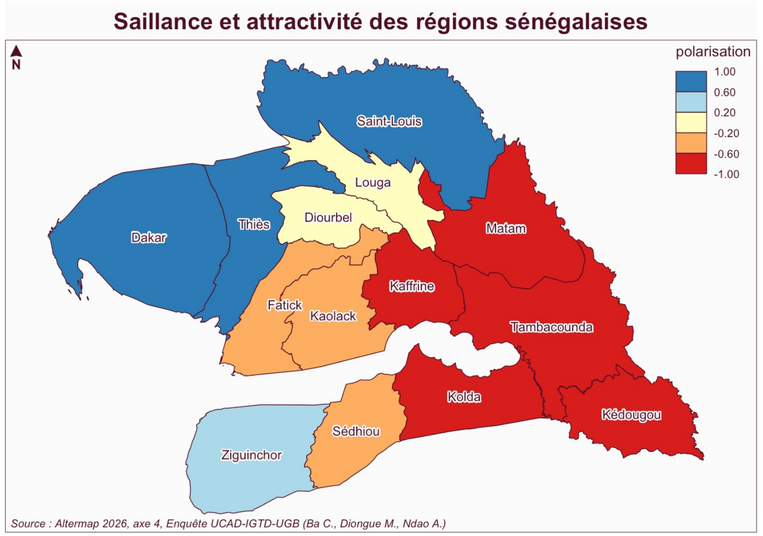

B. Les axes d'expérimentation de la phase test

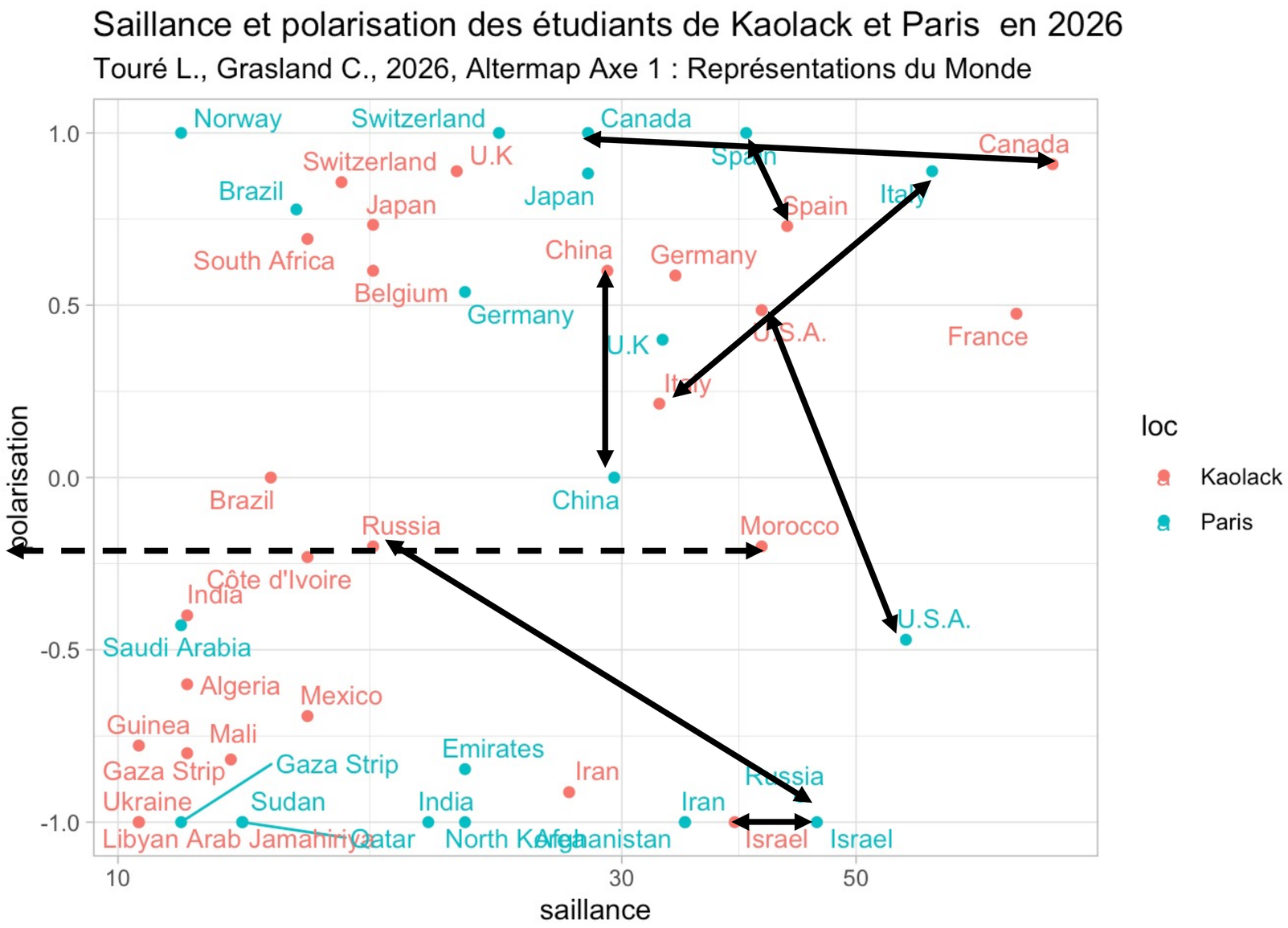

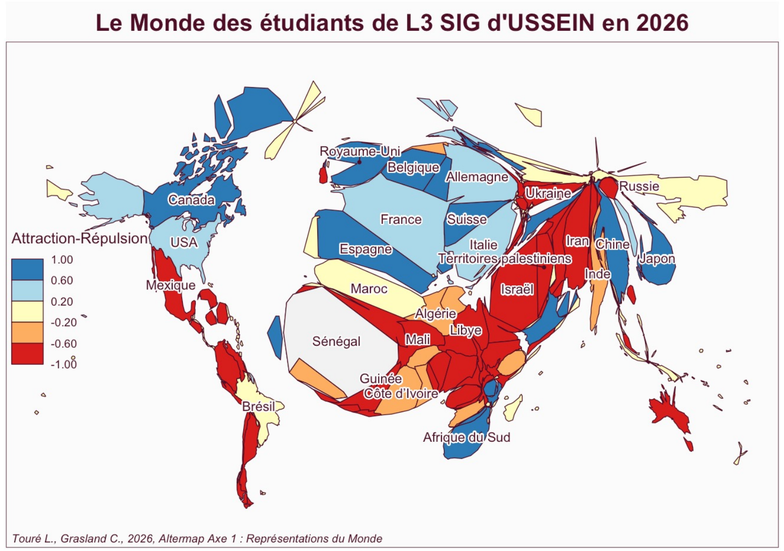

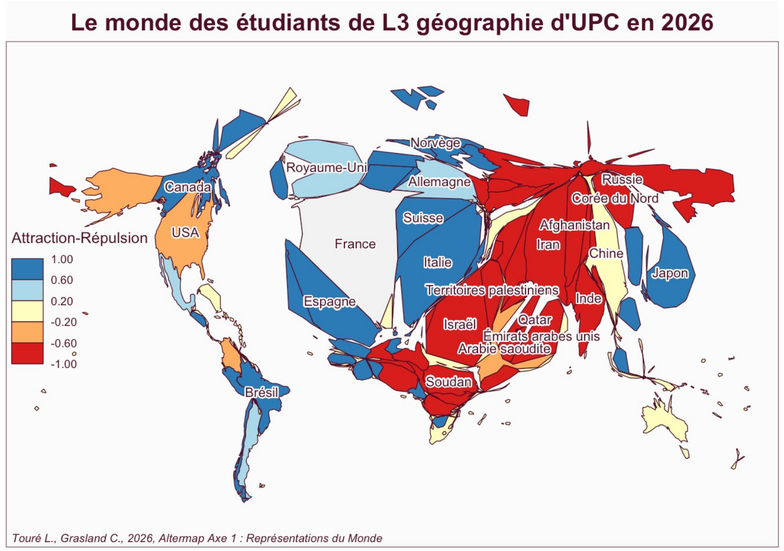

B. Les axes d'expérimentation de la phase test

Noms de région comprenant Fouta* (16 étudiants)

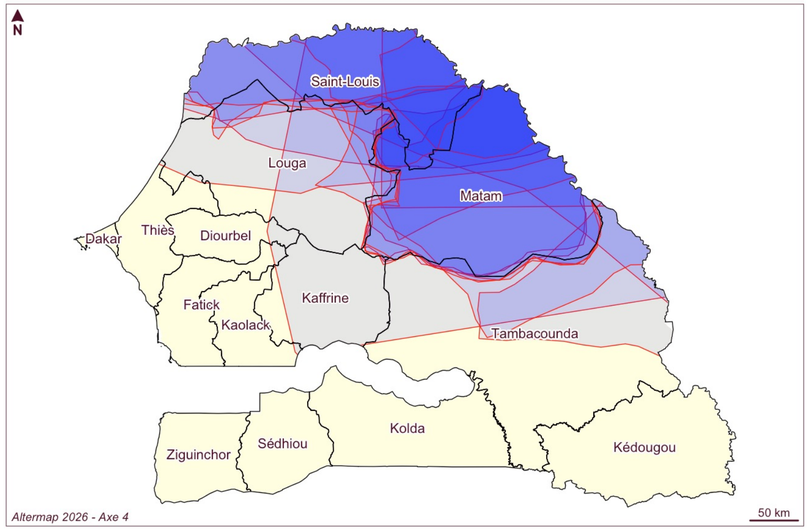

Noms de région comprenant arach* (25 étudiants)

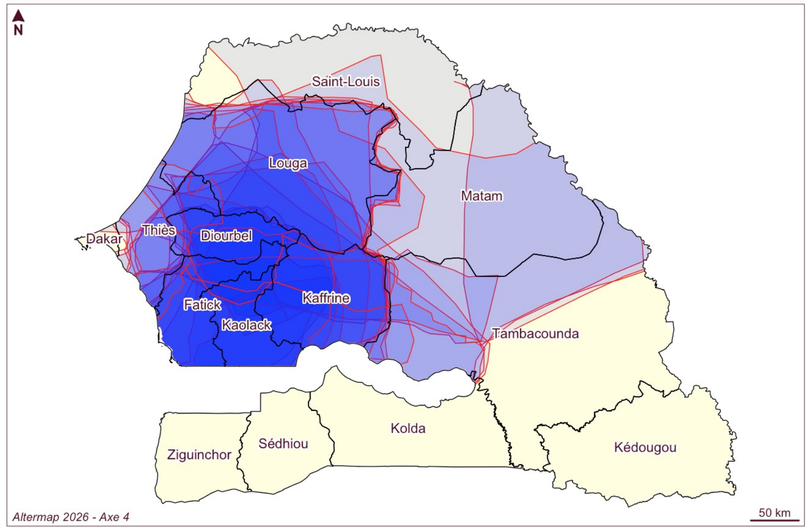

Noms de région comprenant Sine ou Saloun (20 étudiants)

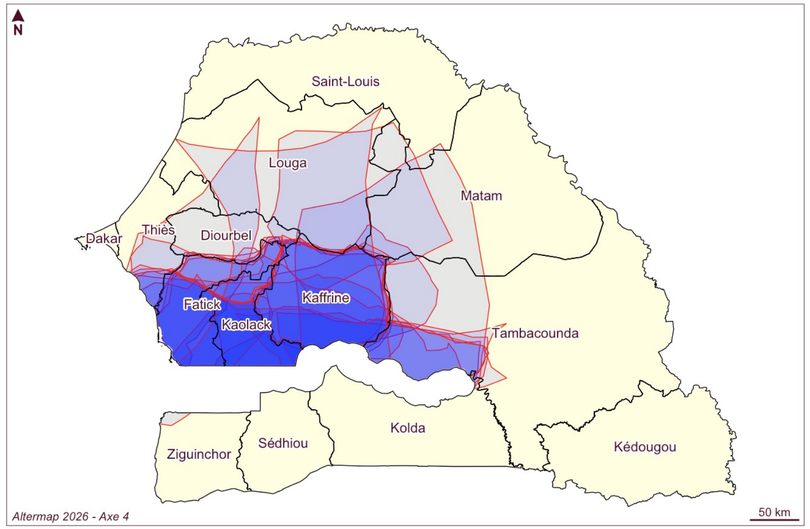

Noms de région comprenant louis* (19 étudiants)

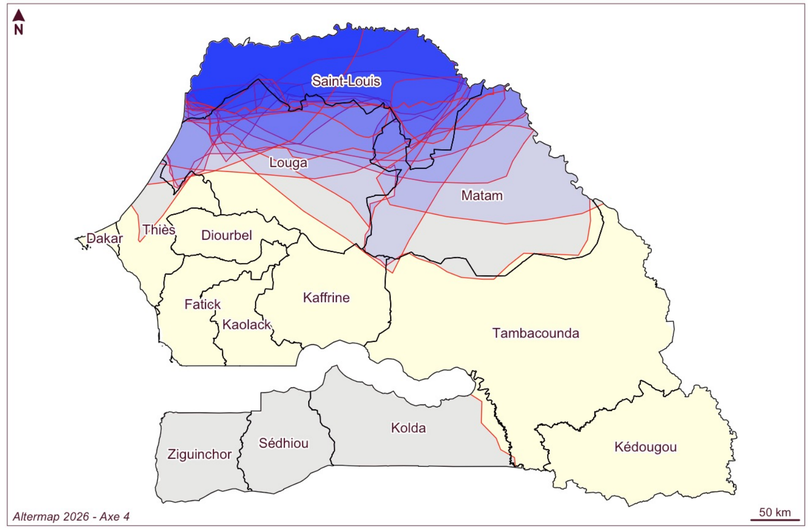

Noms de région comprenant daka* (27 étudiants)

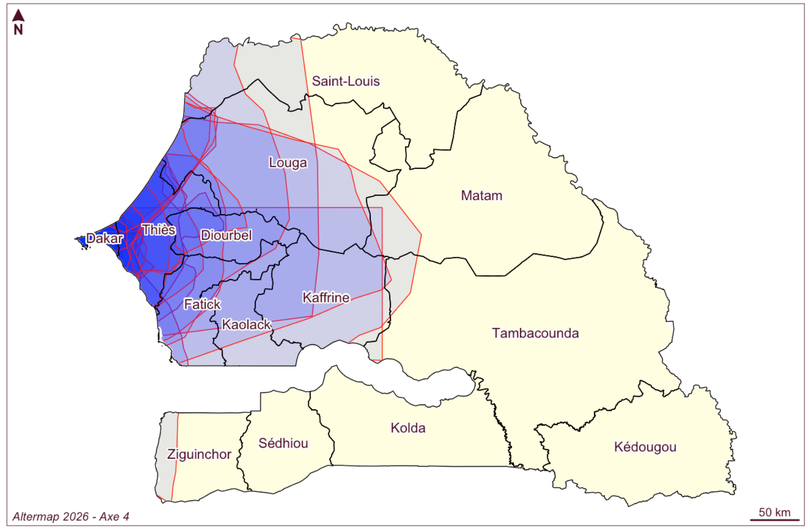

Noms de région comprenant casa (47 étudiants)

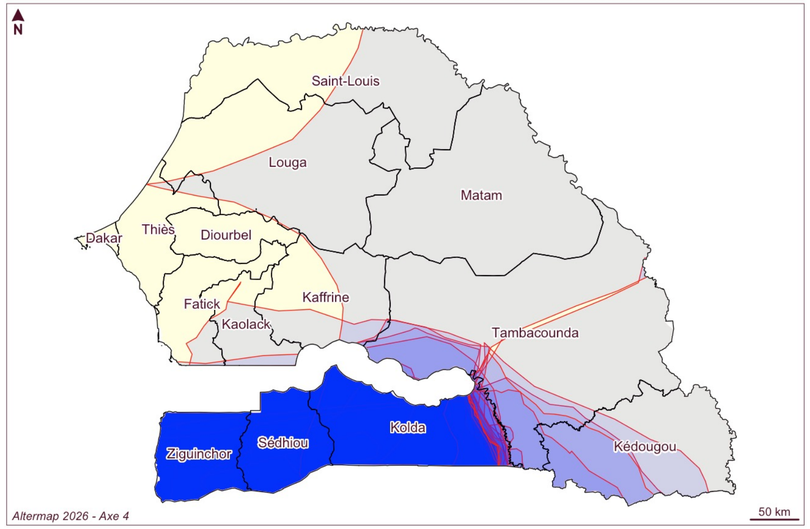

B. Les axes d'expérimentation de la phase test

Superposition des tracés de régions

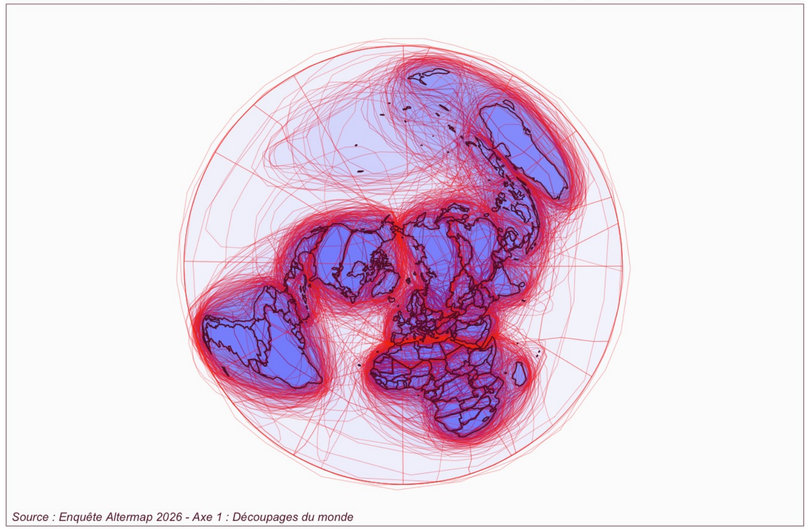

Probabilité de présence d'une frontière

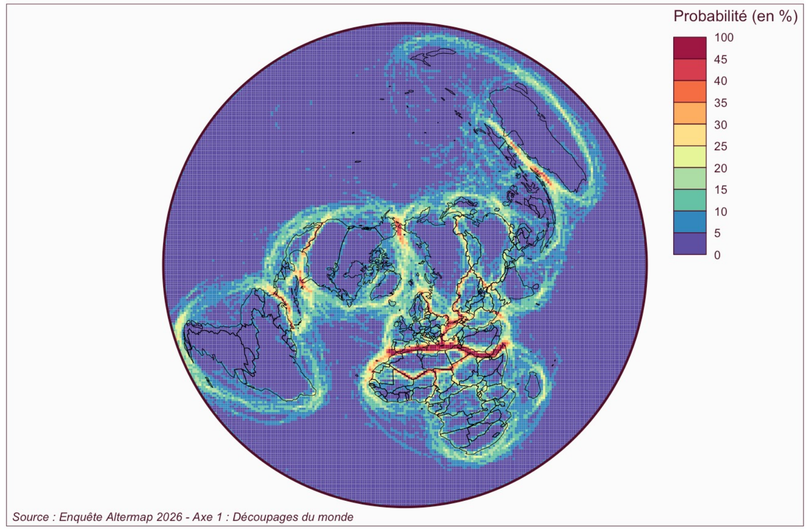

Localisation des 'coeur' régionaux

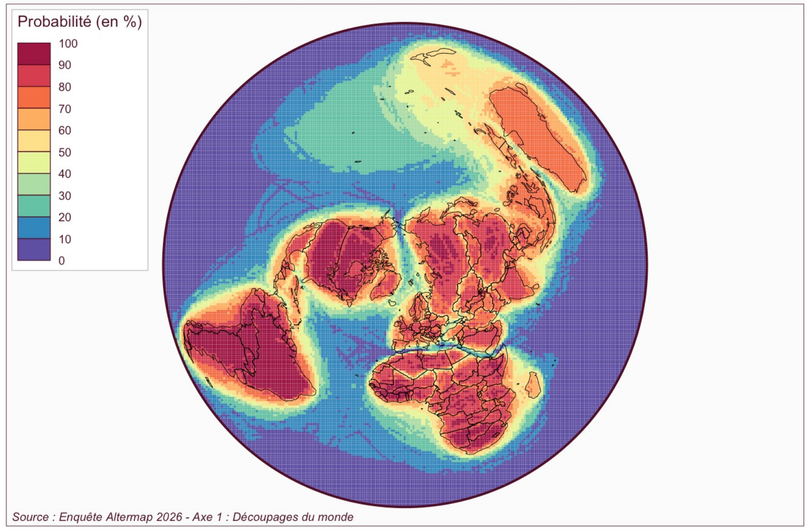

Superposition des tracés de régions (Méditerranée)



Probabilité de présence d'une frontière (zoom)

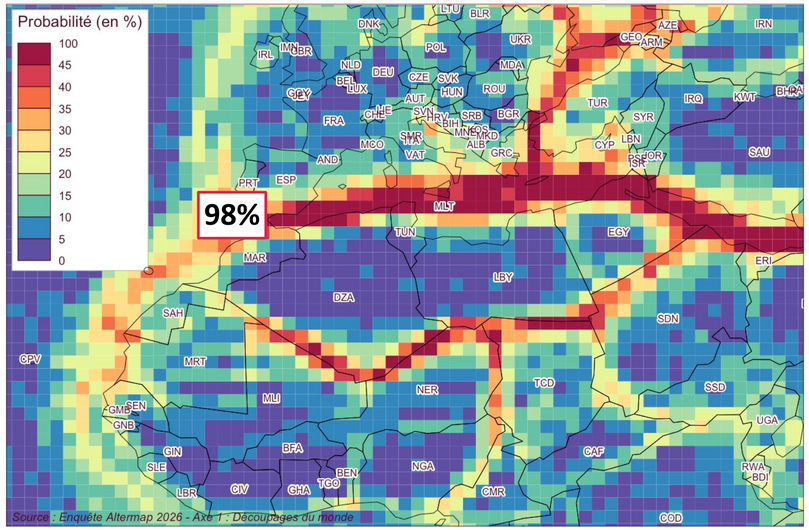

Localisation des 'coeur' régionaux

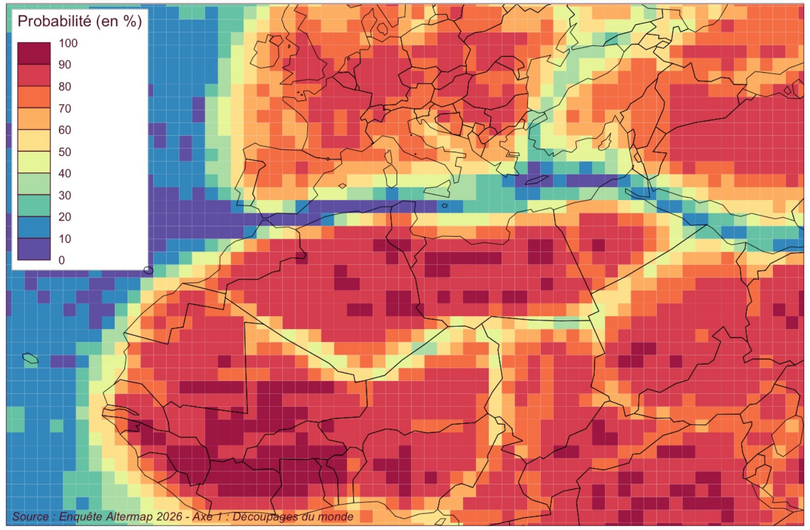

B. Les axes d'expérimentation de la phase test

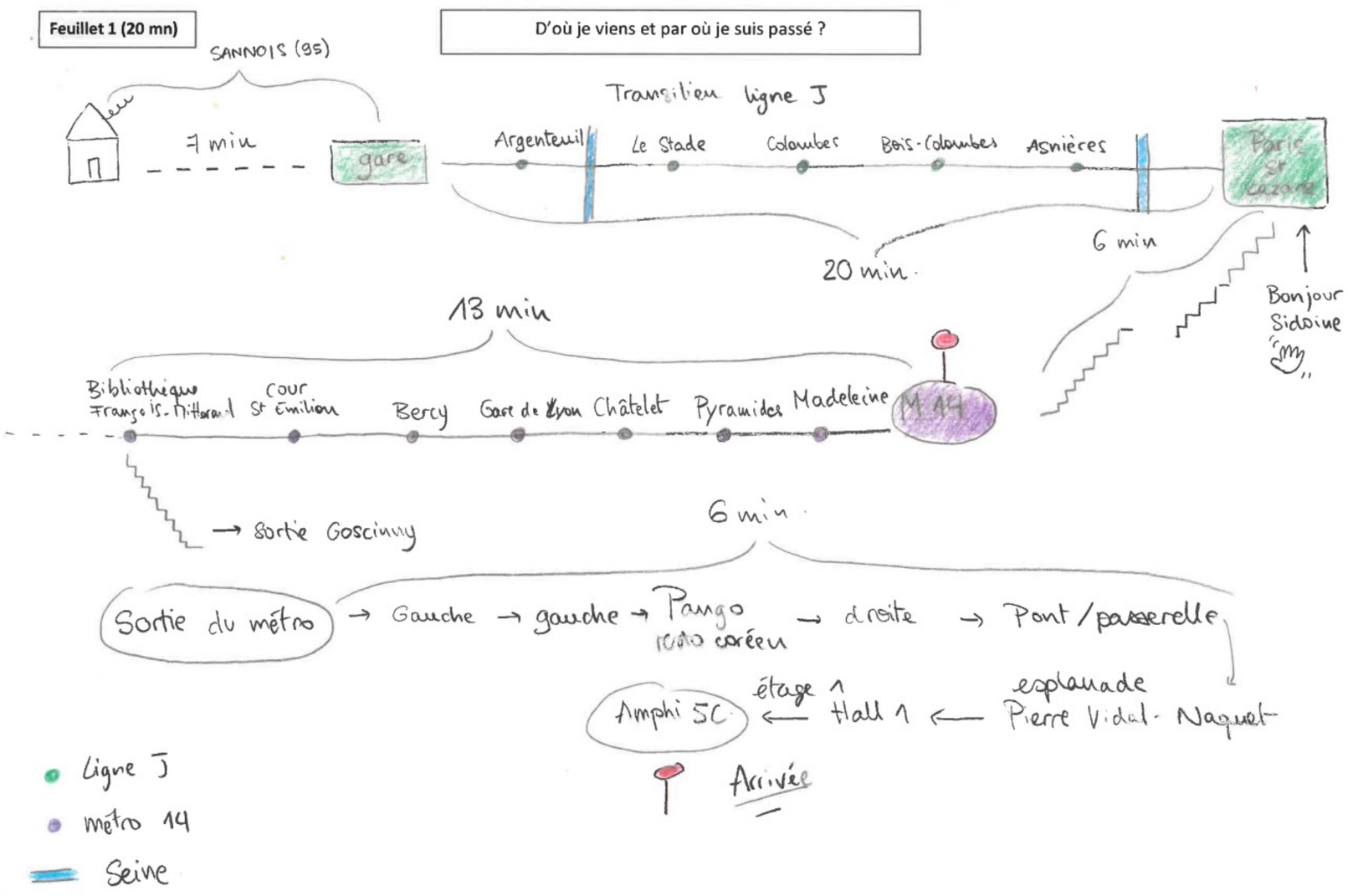

B. Les axes d'expérimentation de la phase test

Feuillet 1 (20 mn)

D'où je viens et par où je suis passé ?

B. Les axes d'expérimentation de la phase test

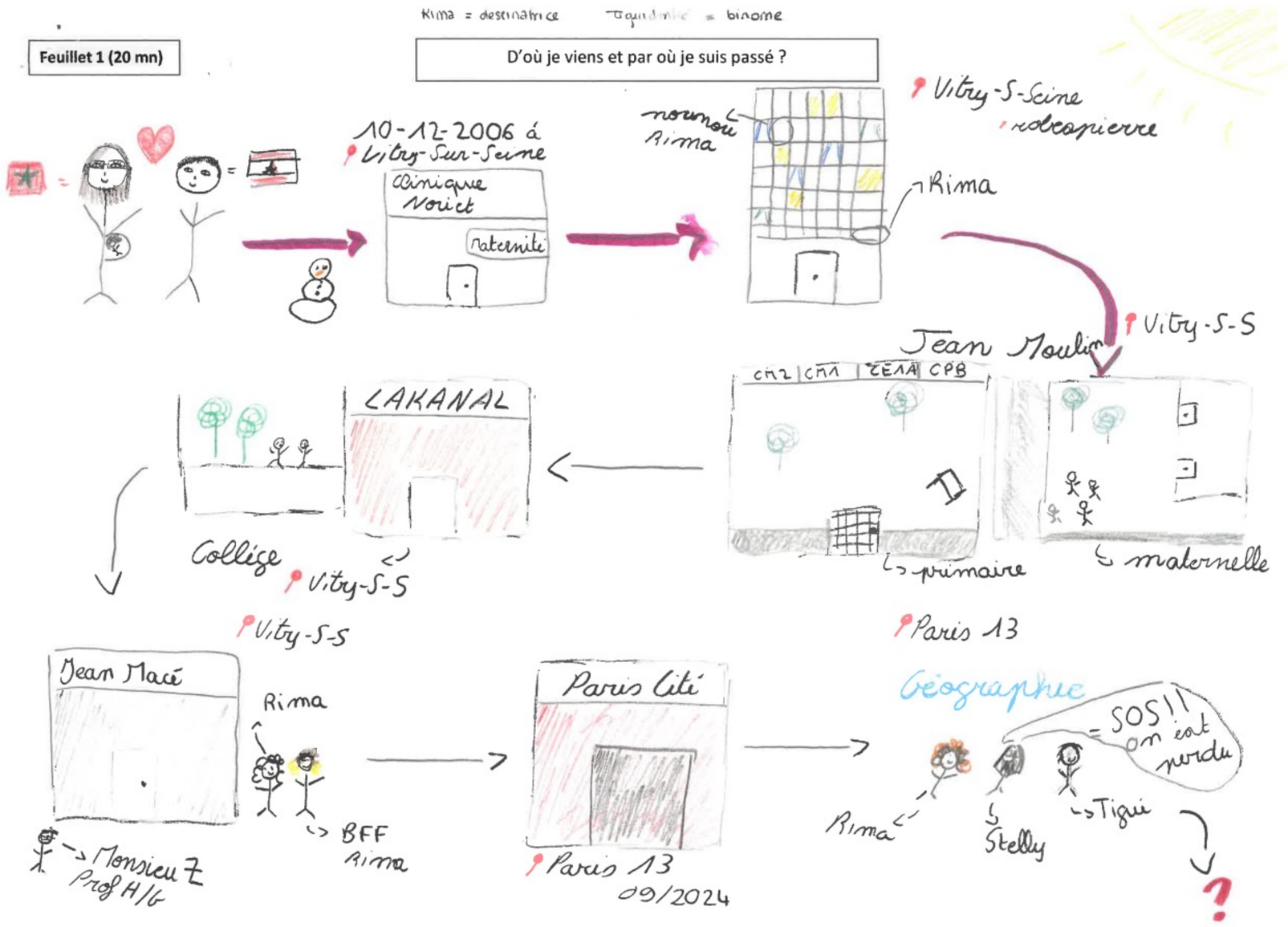

B. Les axes d'expérimentation de la phase test

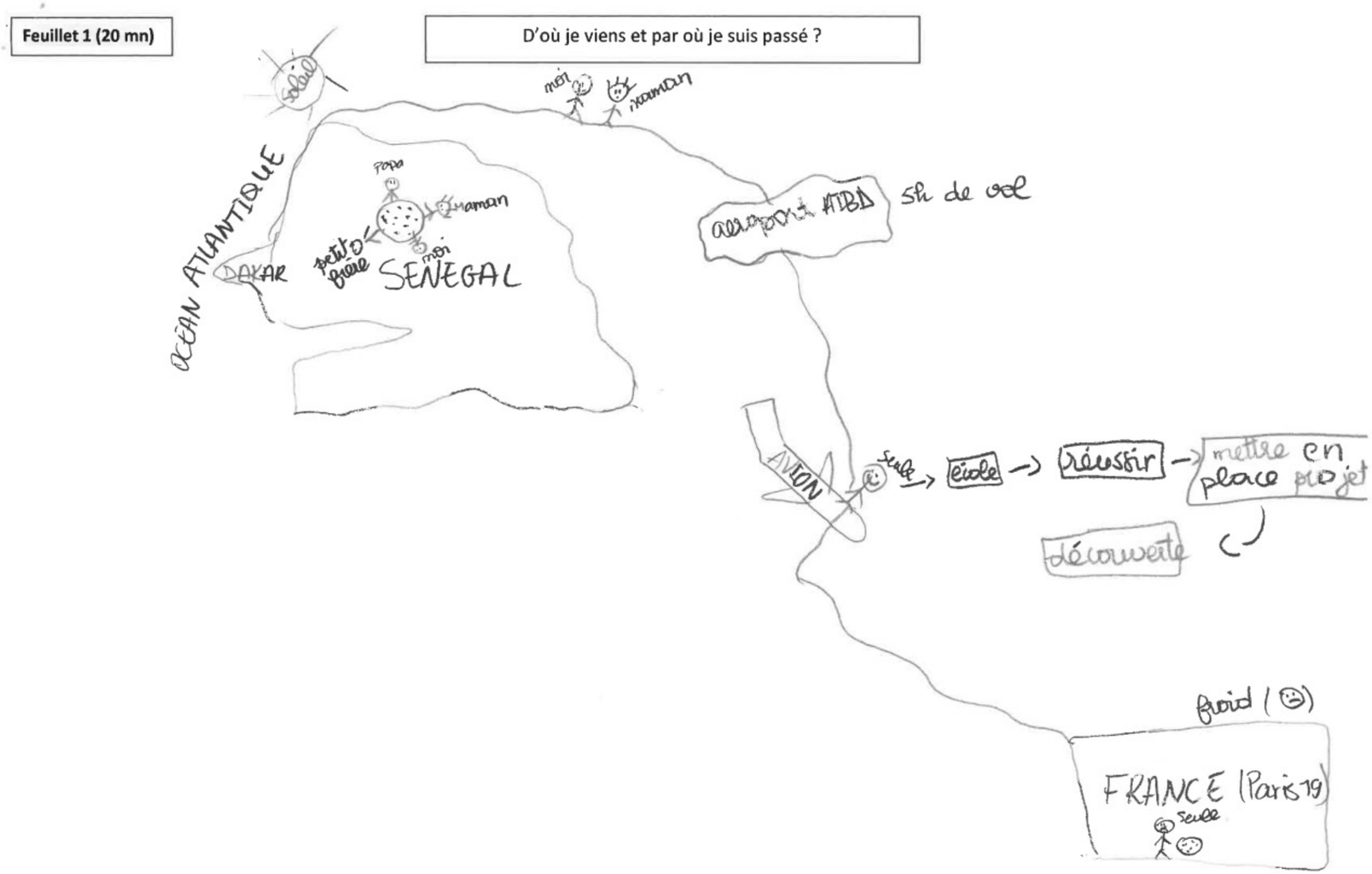

B. Les axes d'expérimentation de la phase test

Feuillet 1 (20 mn)

D'où je viens et par où je suis passé ?

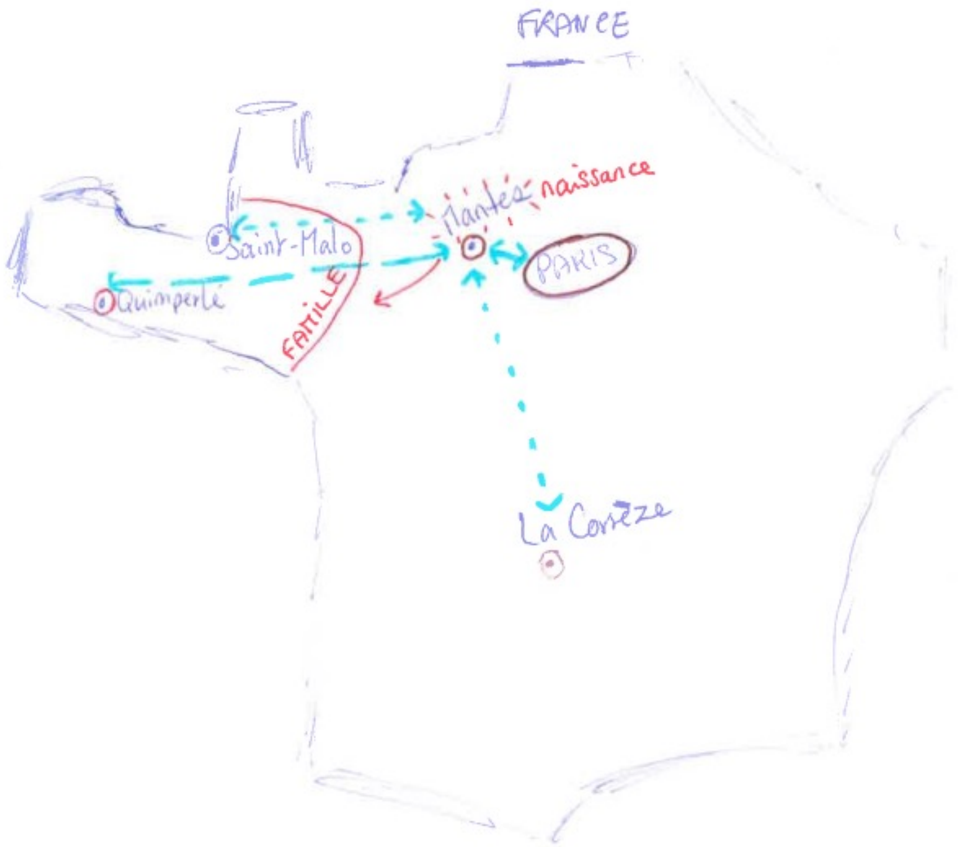

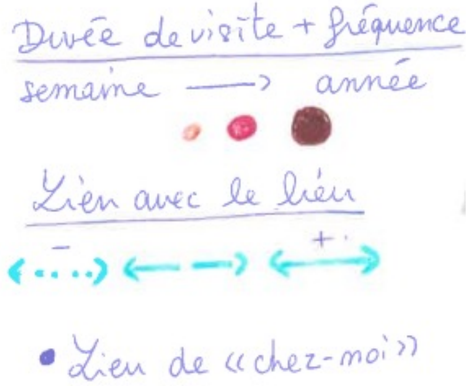

C. Les limites et les perspectives

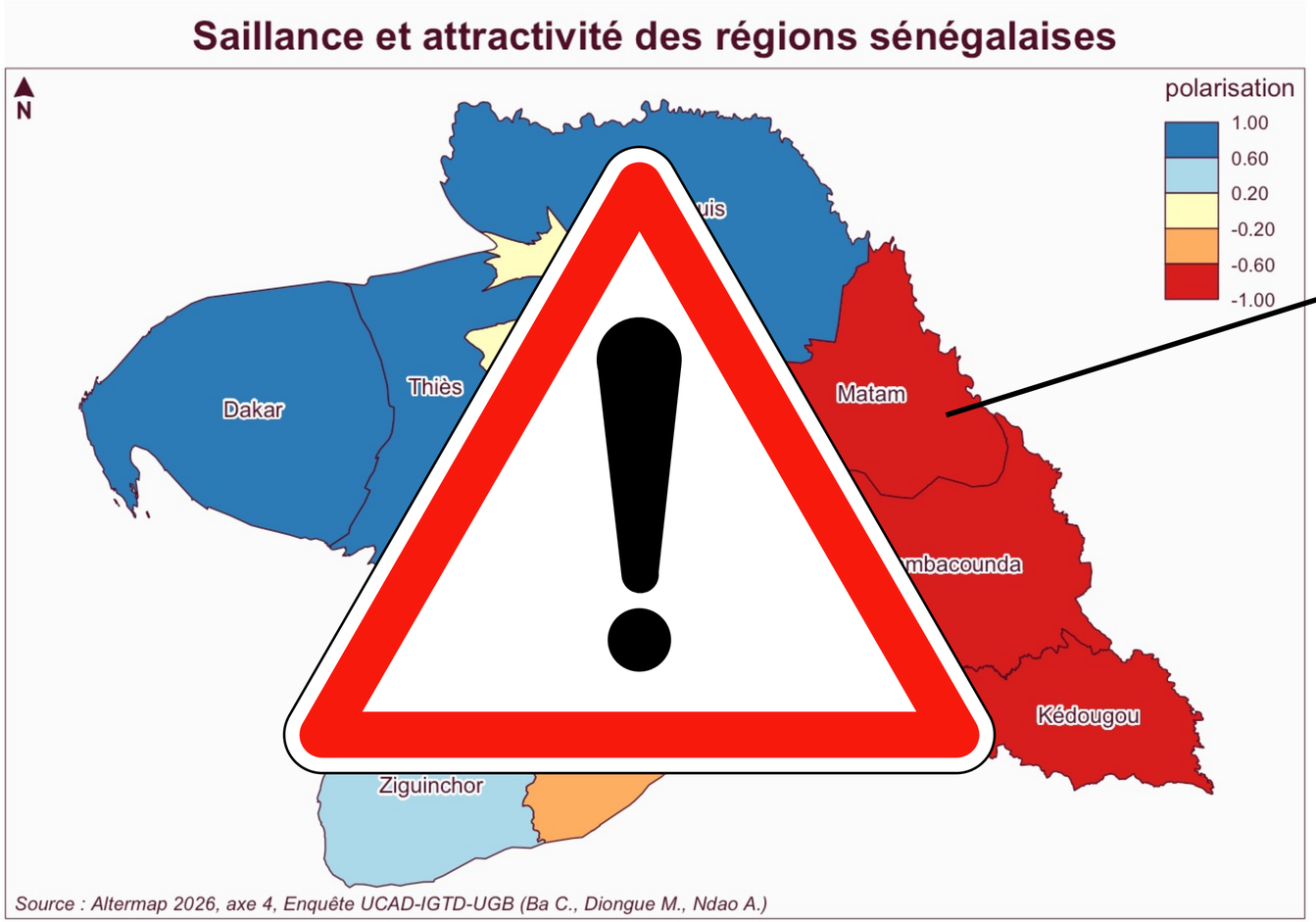

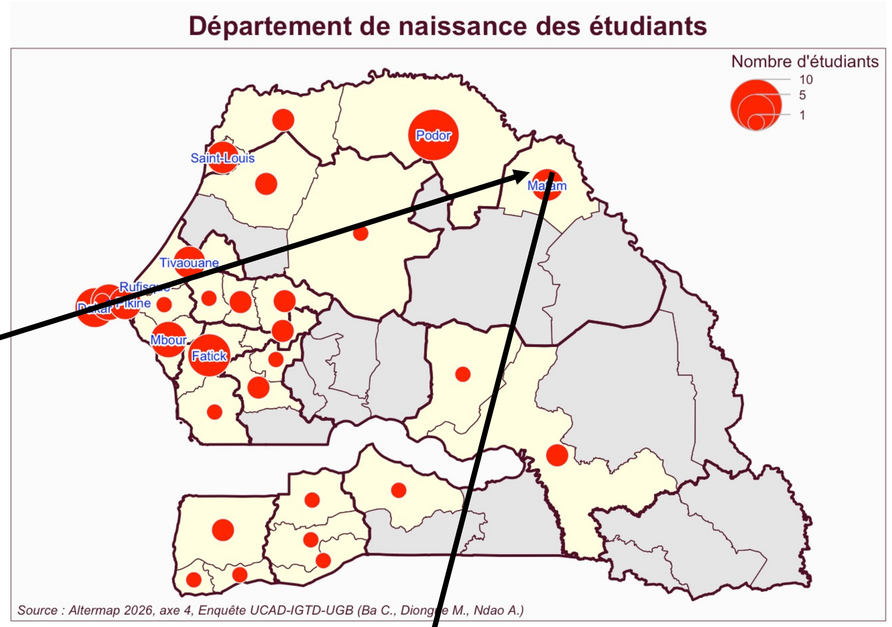

Etudiants nés à Matam

Attraction-répulsion des étudiants nés à Tambaocounda

code	sexe	age	nais_dept	att1	att2	att3	rep1	rep2	rep3
L1017	Une femme	20	SN.MT.MT	Dakar	Matam	Saint-Louis	Tambacounda	Kédougou	Louga
L1037	Une femme	20	SN.MT.MT	Dakar	Matam	Saint-Louis	Tambacounda	Falick	Sédhiou
L1917	Une femme	20	SN.MT.MT	Dakar	Matam	Thiès	Tambacounda	Louga	Kolda
L2021	Un homme	22	SN.MT.MT	Matam	Dakar	Saint-Louis	Tambacounda	Zinguichor	Kédougou

- **Commentaire** : les 4 étudiants nés à Matam déclarent tous vouloir vivre à Dakar ou Matam dans leurs deux premiers choix, puis en troisième lieu à Saint-Louis ou Thiès. En revanche ils rejettent tous en premier Tambacounda puis d'autres régions de l'Est et du Sud.

C. Les limites et les perspectives

La carte finale

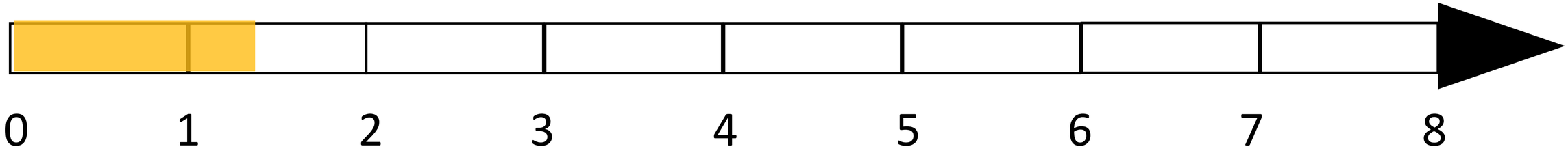

C. Les limites et les perspectives

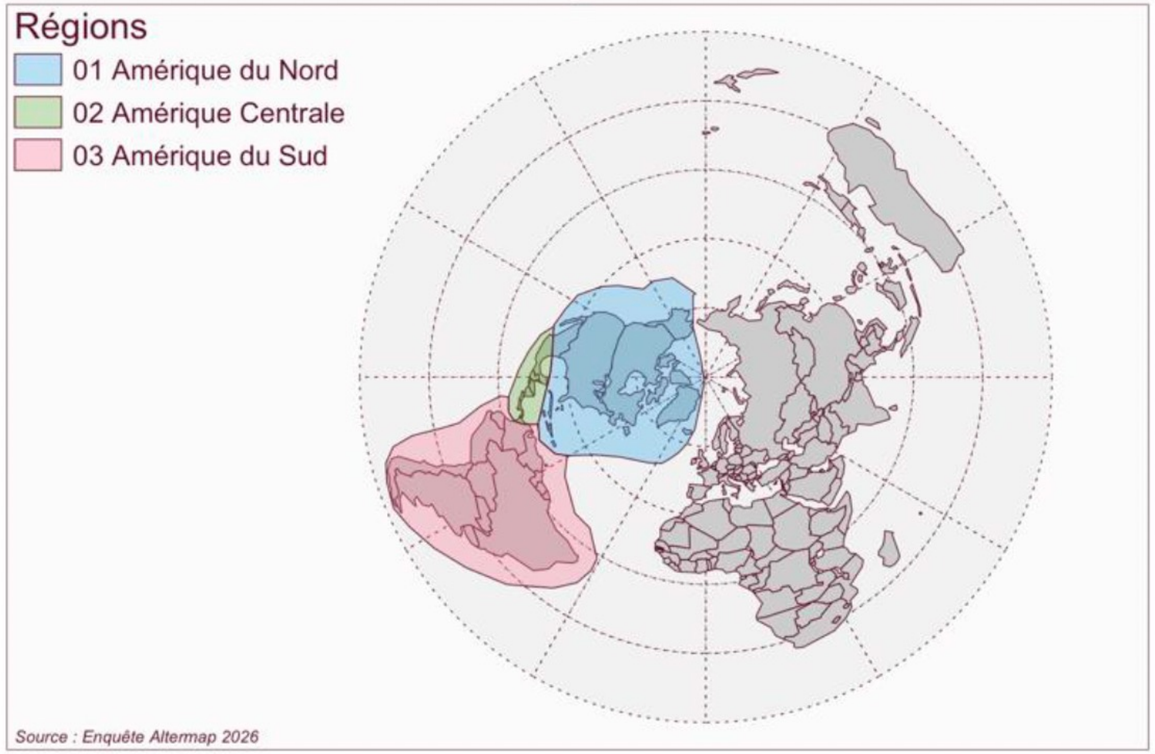

1:41 : D'accord Je mettrais… comme ça… Amérique du Nord. Je pense que je découperais quand même… je mettrai Amérique Centrale… Amérique du Sud

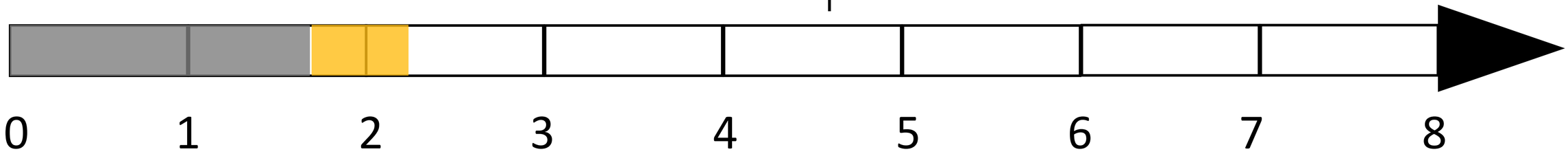

C. Les limites et les perspectives

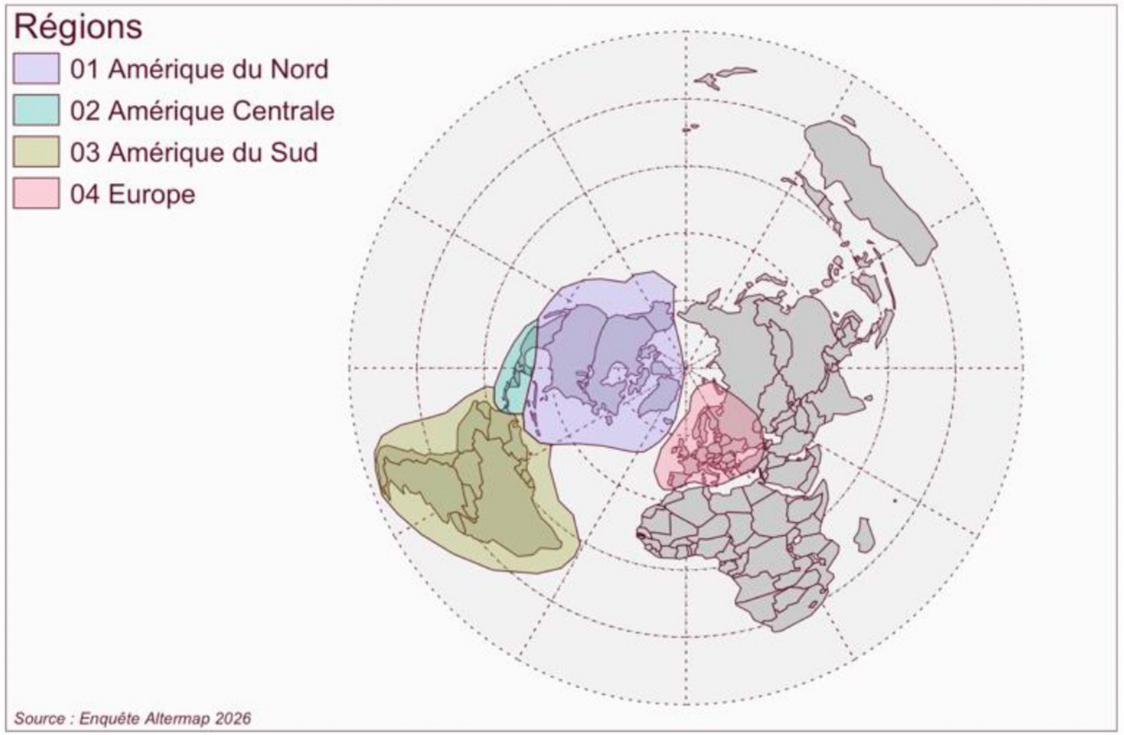

2:20 : Ensuite… Ah, c'est compliqué… on va… Ah, c'est compliqué. Non mais quand même, comment est-ce qu'on découpe l'Europe par exemple ? C'est dur… Hum… On va rester sur une définition classique… Je vais mettre l'Europe… jusqu'au Caucase…. Euh…

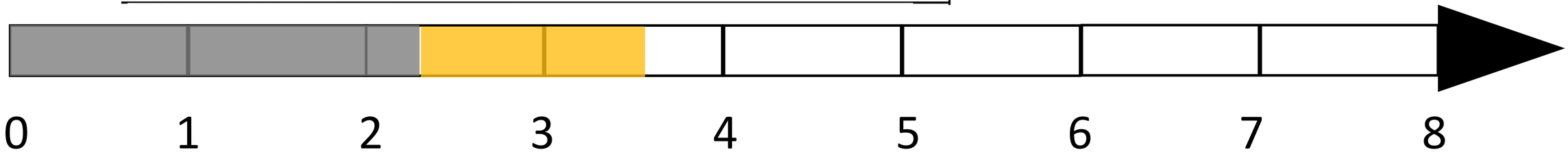

C. Les limites et les perspectives

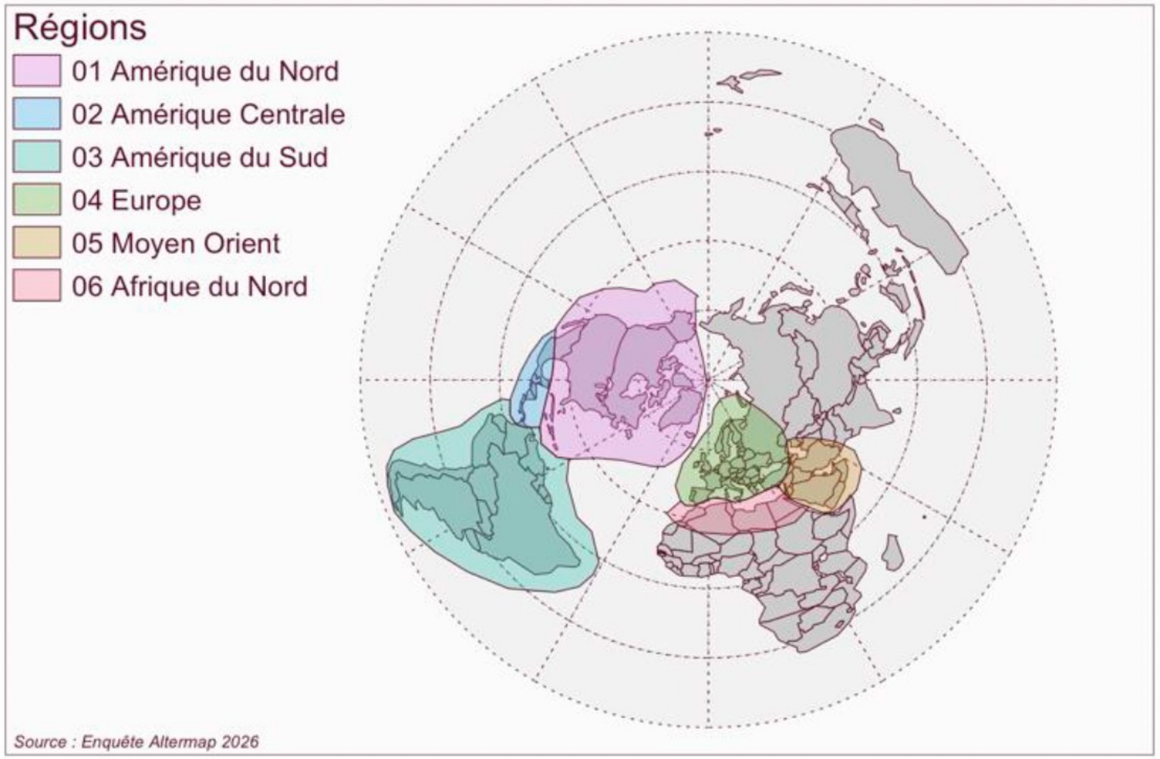

3:30 : Quand même j'inclurais le Moyen-Orient mais je n'inclus pas l'Egypte… J'aurais aussi pu faire… Proche-Orient… Euh… Je ferais l'Afrique du Nord sans l'appeler Maghreb car je pense que l'Egypte c'est pas le Maghreb…

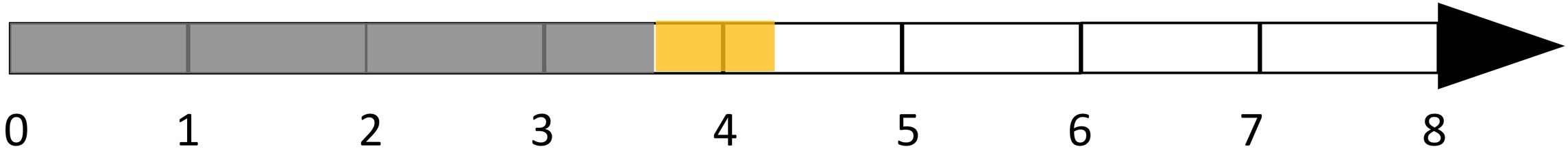

C. Les limites et les perspectives

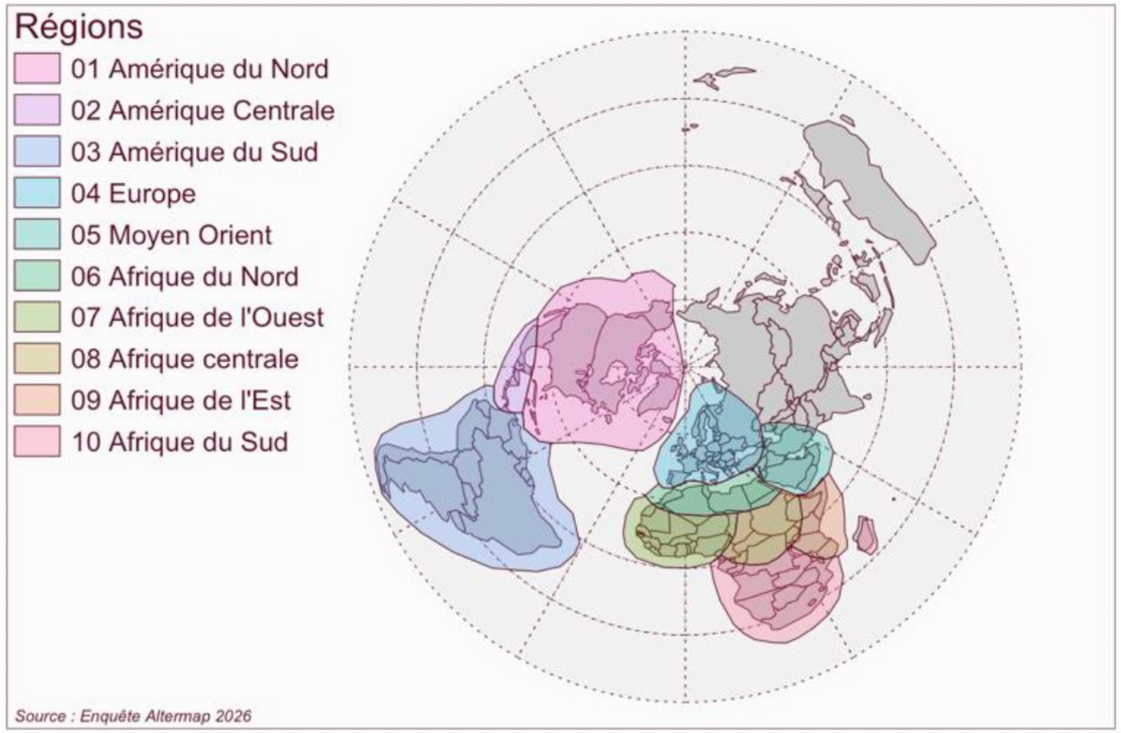

4:00 : Là c'est compliqué… c'est un peu compliqué… Là je pense que déjà on va faire ça… Tac ! … Afrique de l'Ouest. Là c'est plus compliqué parce que pour moi je découperais… je mettrais… mais je ne sais pas forcément les… nommer. Moi je trouve que l'Afrique de l'Est, l'Afrique centrale et l'Afrique du Sud ont des cultures vraiment différentes […]

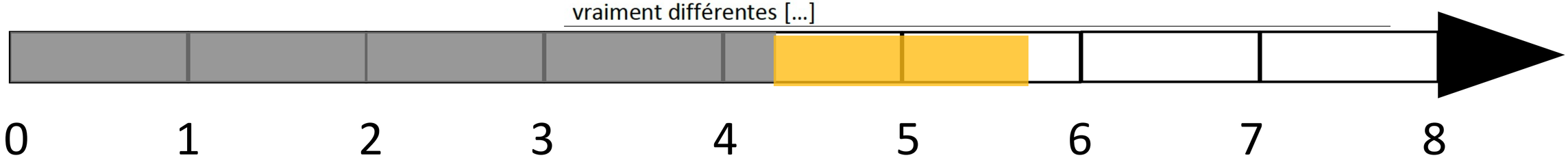

C. Les limites et les perspectives

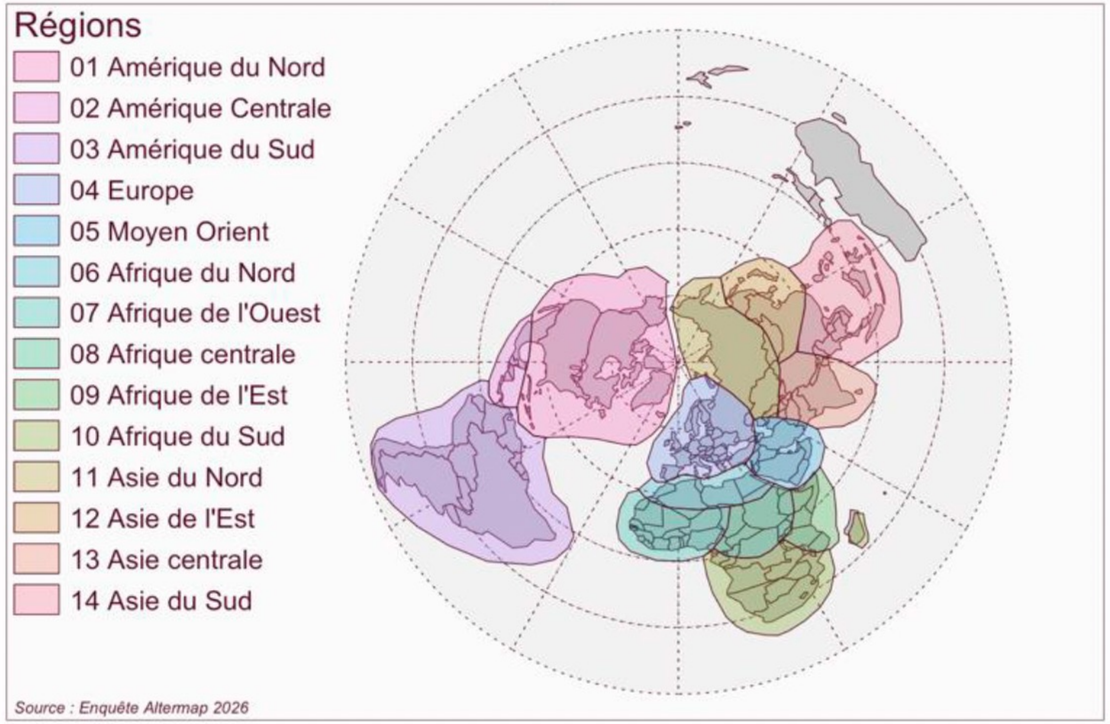

5:43 : Euh … Je pense que je ferais … quelque chose comme ça … Comment est-ce qu'on appelle ça ? … Euh … Asie du Nord… Asie Centrale Ah ! Houla non, … Houla … Plutôt comme ça… et ici je mettrais …. Attendez… Asie de l'Est. Je pense quand même comme ça. Non… C'est pas pour diviser… mais les cultures sont tellement différentes… on ne peut pas toutes les mettre dans le même panier…

0 1 2 3 4 5 6 7 8

C. Les limites et les perspectives

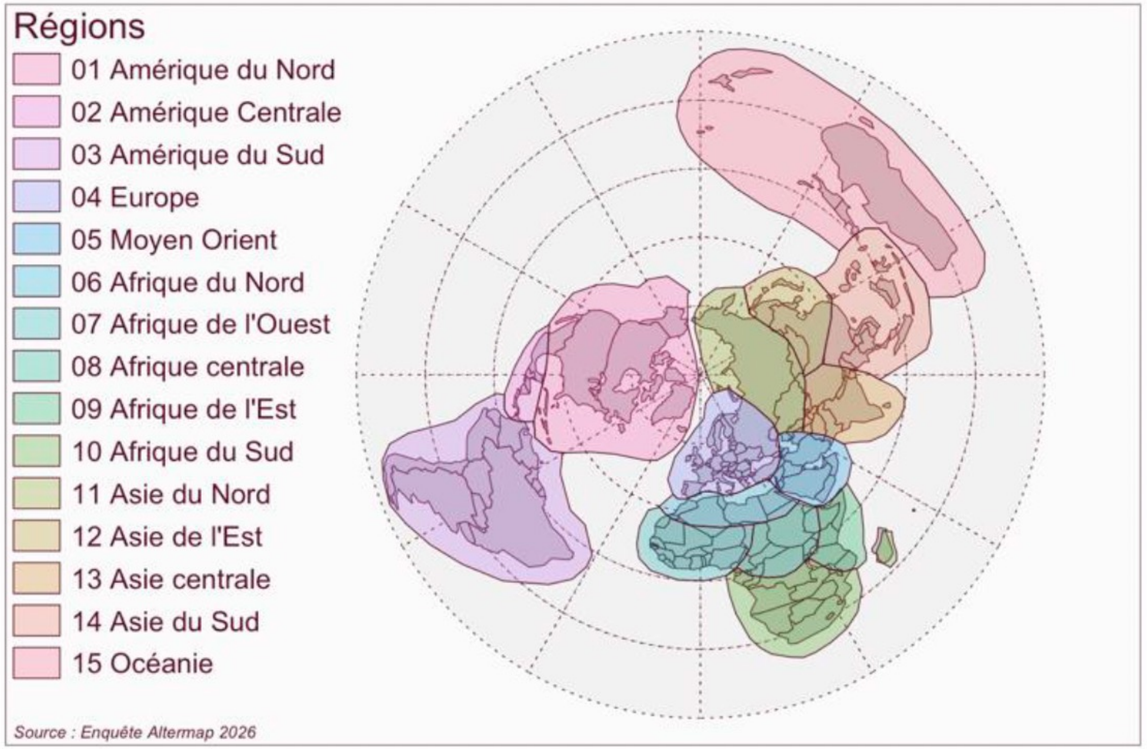

8:24 : Et j'ajoute l'Océanie que je ne connais pas très bien.

9 :00 : ***Enquêteur : merci de votre participation***

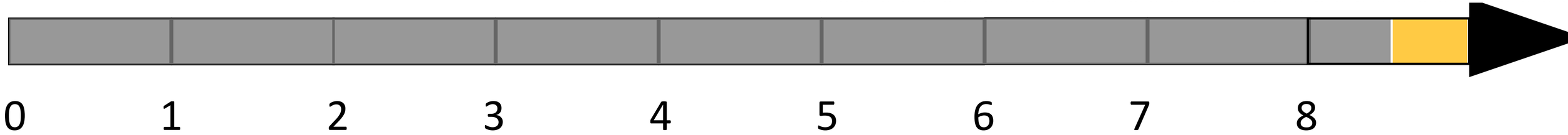

C. Les limites et les perspectives

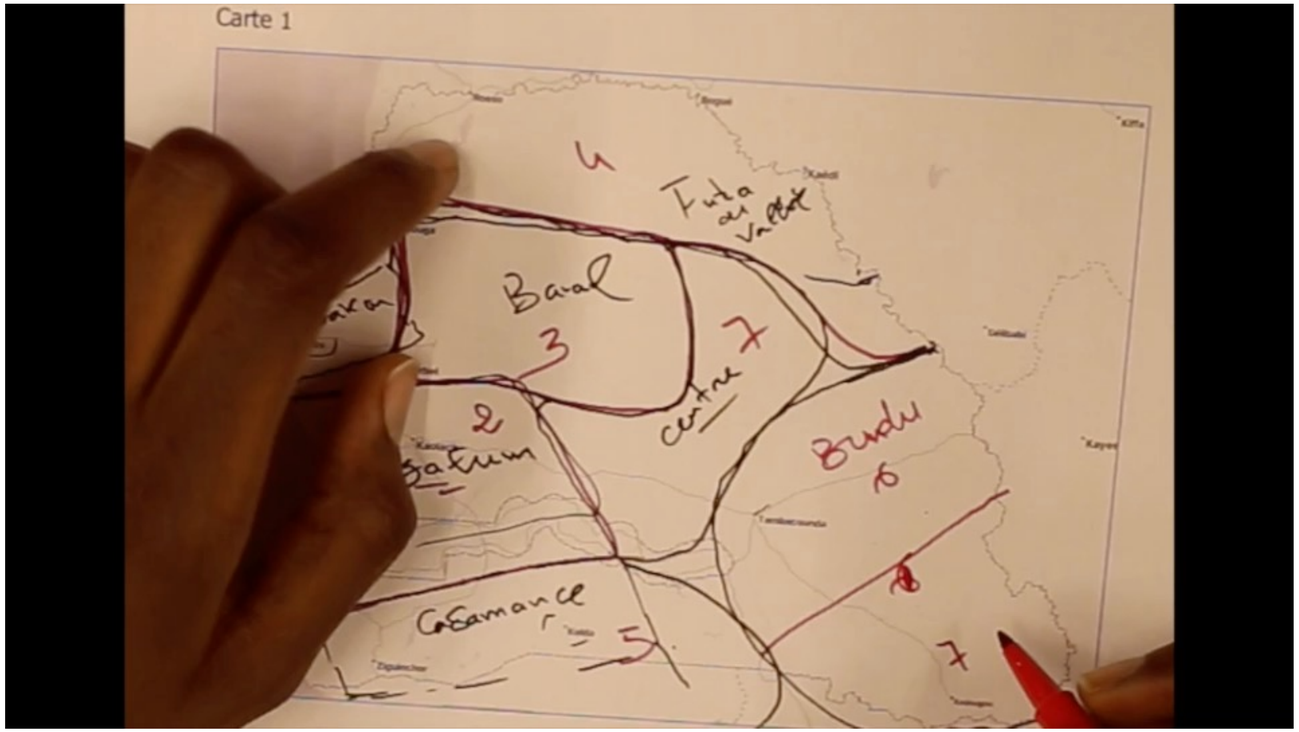

MERCI DE VOTRE ATTENTION

https://worldregio.github.io/altermap/